GUÍA DE USO
SISTEMA DE GESTIÓN, SEGUIMIENTO Y GEORREFERENCIACIÓN DE INICIATIVAS DEL PLAN MAESTRO PARA EL DESARROLLO Y GESTIÓN DE LA INVERSIÓN DE COMUNA DE SAN JOSÉ DE MAIPO

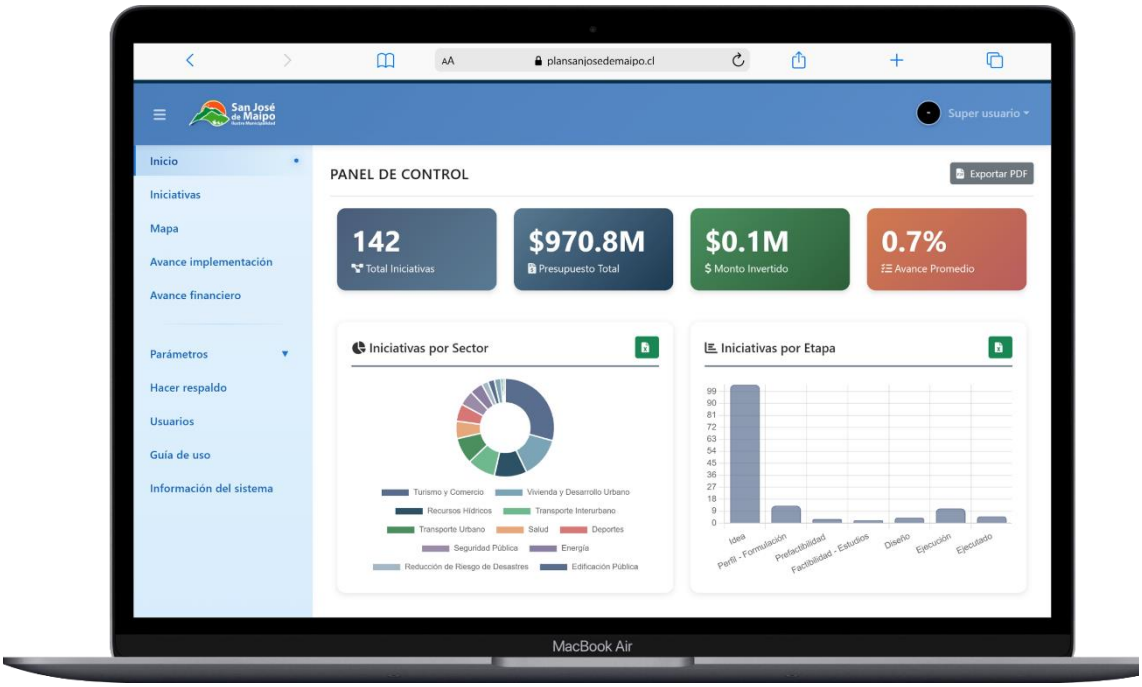

Marzo de 2026

Contenido

GUÍA DE USO SISTEMA DE GESTIÓN, SEGUIMIENTO Y GEORREFERENCIACIÓN DE INICIATIVAS DEL PLAN MAESTRO PARA EL DESARROLLO Y GESTIÓN DE LA INVERSIÓN DE COMUNA DE SAN JOSÉ DE MAIPO 1

Introducción 3

Ventajas 3

Sobre el inicio de sesión y los datos de acceso 5

El panel de control 6

Gestión de iniciativas 8

Informe de estado de avance de implementación 12

Informe de avance financiero 14

Parámetros del sistema 15

Mapa interactivo 17

Respaldo de base de datos 18

Gestión de usuarios 19

Áreas asignadas 20

Perfiles de usuario 21

Información del sistema 21

Consideraciones finales 22

Introducción

El sistema para la gestión, seguimiento y georreferenciación de los proyectos del Plan de la Comuna de San José de Maipo es un software de entorno web diseñado para administrar y visualizar información sobre iniciativas y proyectos asociados al Plan. El sistema permite la gestión integral de los datos de las iniciativas, posibilitando la creación de nuevos proyectos, la actualización de la información existente y el seguimiento de cada uno de ellos. Además, cuenta con un sistema de gestión y acceso de usuarios con dos perfiles distintos, asegurando un control adecuado sobre la información. Cada iniciativa puede tener asociadas actividades específicas, lo que permite hacer un seguimiento detallado de su desarrollo y evaluar su progreso en el tiempo. Asimismo, el sistema facilita la creación de indicadores vinculados a cada iniciativa, proporcionando herramientas para medir su impacto y evolución.

Asociado a la información de las iniciativas, el sistema cuenta con un mapa interactivo que presenta de manera georreferenciada la ubicación de cada proyecto. Este mapa permite a la ciudadanía visualizar los lugares donde se desarrollarán las iniciativas y acceder al detalle de cada una de ellas, incluyendo información sobre el área a la que pertenecen, su fuente de financiamiento, la unidad responsable, su estado de avance, entre otros aspectos relevantes.

Cada ubicación en el mapa es representada por un círculo de color, donde cada color indica un área de clasificación. Dentro de cada círculo, un número indica la cantidad de proyectos asociados a una ubicación en particular.

El municipio, por su parte, puede gestionar toda la información contenida en la aplicación a través del sistema de administración, al cual se accede mediante credenciales de usuario. Esto permite controlar los datos que se muestran a la ciudadanía a través del mapa interactivo, garantizando que la información publicada sea precisa y actualizada.

Los datos de los proyectos se cargan previamente en la plataforma, de modo que la aplicación esté lista para su uso. El personal municipal es responsable de actualizar la información a medida que los proyectos evolucionan, especialmente en lo que respecta a su estado de avance.

El acceso al mapa está disponible a través de un enlace en la página web del municipio. Los usuarios pueden consultarlo desde cualquier dispositivo con conexión a internet, ya sea un computador, una tableta o un teléfono móvil, sin importar su marca o modelo.

Ventajas

La implementación de este sistema ofrece varias ventajas significativas:

1. Gestión eficiente de los datos: Permite la administración centralizada de toda la información de los proyectos, asegurando que los datos sean accesibles y modificables por el personal autorizado en cualquier momento.

2. Seguimiento detallado de iniciativas: Proporciona herramientas para registrar y analizar el desarrollo de cada iniciativa, permitiendo evaluar el progreso y tomar decisiones informadas sobre su ejecución.

3. Creación y actualización de indicadores: Posibilita la generación de indicadores clave para medir el impacto y la evolución de cada iniciativa, facilitando la evaluación de su desempeño.

4. Acceso fácil y rápido a la información: La ciudadanía puede acceder de forma sencilla a través de cualquier dispositivo conectado a Internet, lo que facilita el acceso a la información de los proyectos desde cualquier lugar y en cualquier momento. No importa si se utiliza un computador, un Tablet o un teléfono móvil, ya que el sistema es compatible con múltiples dispositivos.

5. Visualización clara y comprensible: Mediante el uso de un mapa interactivo, los usuarios pueden tener una visión clara y comprensible de la ubicación de los proyectos en San José de Maipo. Los círculos de colores y los números asociados a cada ubicación facilitan la identificación y comprensión de la cantidad de proyectos en una determinada área de clasificación.

6. Información detallada y actualizada: El sistema proporciona información detallada sobre cada proyecto, incluyendo el área a la que pertenece, la fuente de financiamiento, la unidad municipal responsable y el estado de avance. Además, gracias al sistema de gestión de datos, el personal municipal puede mantener la información actualizada, lo que garantiza que la ciudadanía acceda a datos precisos y fiables en todo momento.

7. Filtrado y personalización de la información: Los usuarios tienen la capacidad de filtrar los datos según sus intereses específicos. Pueden seleccionar áreas de clasificación específicas, tipos de iniciativas o cualquier otro parámetro relevante para obtener información personalizada y relevante para ellos. Esto les permite centrarse en los proyectos que les interesan y obtener una visión más precisa de su estado y ubicación.

8. Transparencia y participación ciudadana: El sistema fomenta la transparencia al brindar acceso público a la información sobre los proyectos del Plan Maestro. Los ciudadanos pueden conocer de manera clara y transparente cómo se están desarrollando los proyectos en su comuna, lo que promueve la participación ciudadana informada y facilita la colaboración entre la municipalidad y la comunidad.

Sobre el inicio de sesión y los datos de acceso

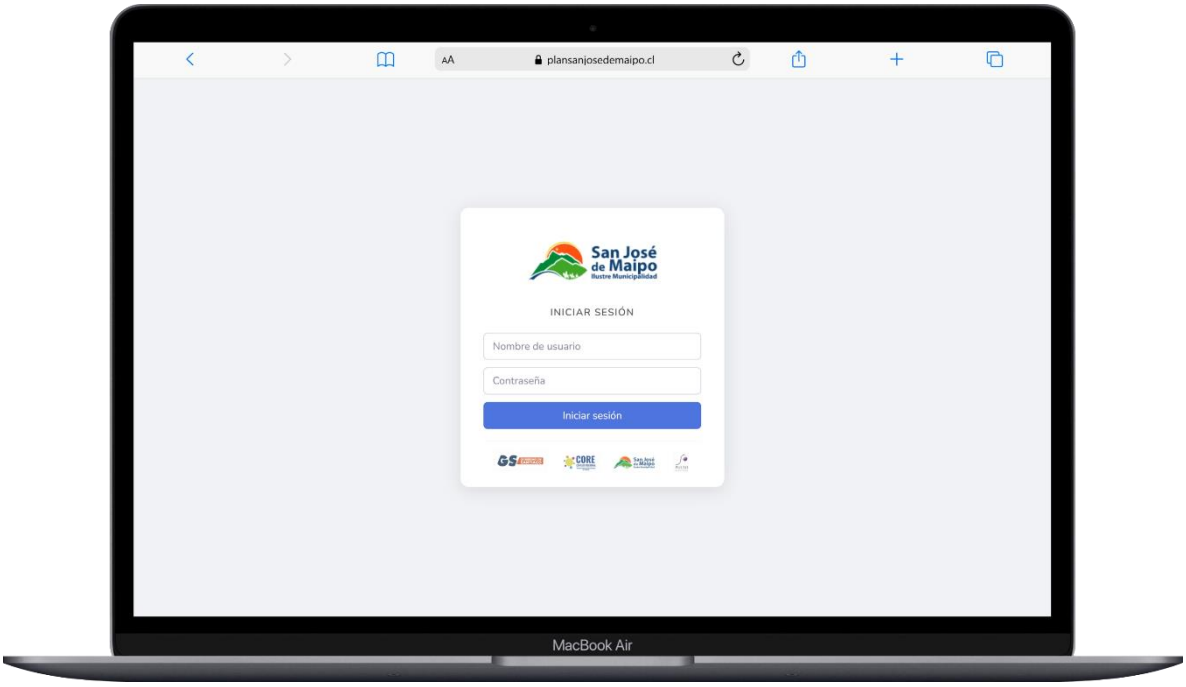

El acceso al sistema se realiza mediante credenciales personales compuestas por un nombre de usuario y una contraseña. Estas credenciales son proporcionadas inicialmente por el administrador del sistema, quien entrega a cada usuario una cuenta previamente creada para permitir su acceso a la plataforma.

Una vez que el usuario recibe sus datos de acceso, puede ingresar al sistema desde la pantalla de inicio de sesión utilizando dichas credenciales. Por motivos de seguridad, se recomienda que el usuario cambie su contraseña en el primer acceso o cuando lo estime necesario. El sistema permite a cada usuario modificar su propia contraseña en cualquier momento a través de las opciones disponibles en su perfil.

La administración de cuentas de usuario es responsabilidad del usuario con perfil de administrador. Este perfil tiene la capacidad de crear nuevas cuentas, modificar los datos de usuarios existentes y gestionar los permisos de acceso dentro del sistema. Esto permite adaptar la plataforma a las necesidades organizacionales del municipio a medida que nuevos funcionarios requieren acceso o cambian sus responsabilidades.

Cada usuario del sistema se encuentra asociado a uno o más instrumentos dentro de la estructura organizacional definida en la plataforma. Esta asociación cumple una función clave en la gestión de permisos, ya que determina qué iniciativas o proyectos pueden ser editados por cada usuario. De esta forma, un usuario solo podrá modificar la información de aquellos proyectos que pertenezcan al instrumento al que está vinculado, mientras que las iniciativas de otros instrumentos permanecerán disponibles únicamente para consulta o fuera de su ámbito de edición.

Este mecanismo permite mantener un control ordenado sobre la gestión de la información, evitando modificaciones no autorizadas y asegurando que cada unidad o departamento sea responsable de la actualización de sus propias iniciativas.

El perfil de administrador dispone de privilegios ampliados dentro del sistema. Además de poder crear y gestionar usuarios, tiene acceso completo a la información de todos los proyectos registrados en la plataforma, independientemente del área a la que pertenezcan. Esto le permite supervisar la consistencia de los datos, apoyar a las distintas unidades municipales en la gestión de la información y asegurar el correcto funcionamiento general del sistema.

Gracias a esta estructura de acceso basada en usuarios, perfiles e instrumentos, el sistema permite distribuir las responsabilidades de actualización de información entre distintas unidades del municipio, manteniendo al mismo tiempo un adecuado nivel de control y seguridad sobre los datos almacenados.

En caso de que un usuario pierda u olvide sus datos de acceso, deberá contactar al administrador del sistema en el municipio, quien podrá restablecer su contraseña y permitirle recuperar el acceso a la plataforma.

El panel de control

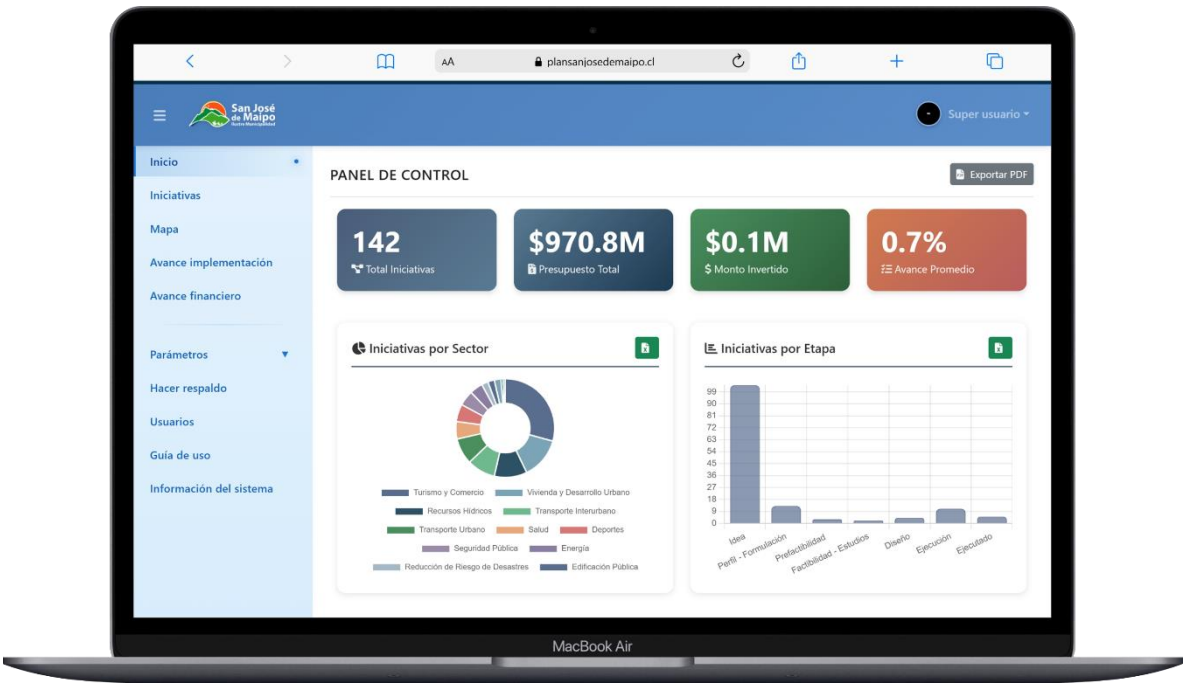

El panel de control corresponde a la pantalla inicial del sistema y tiene como objetivo entregar una visión general del estado de las iniciativas registradas en la plataforma. A través de indicadores resumidos y visualizaciones gráficas, permite conocer rápidamente el volumen de proyectos, su distribución por sector y etapa, así como su nivel de avance físico y financiero.

En la parte superior del panel se presentan cuatro indicadores principales que resumen la situación global de las iniciativas. Estos indicadores muestran el total de iniciativas registradas, el presupuesto total asociado a los proyectos, el monto efectivamente invertido y el avance promedio del conjunto de iniciativas. Estos valores permiten tener una referencia inmediata del estado general del plan de inversión.

Debajo de estos indicadores se incluyen dos visualizaciones gráficas. La primera corresponde a “Iniciativas por sector”, representada mediante un gráfico circular que muestra la distribución de los proyectos según el sector o área temática a la que pertenecen, por ejemplo turismo y comercio, vivienda y desarrollo urbano, recursos naturales y medio ambiente, entre otros. Esta visualización permite identificar rápidamente qué sectores concentran una mayor cantidad de iniciativas.

La segunda visualización corresponde a “Iniciativas por etapa”, presentada mediante un gráfico de barras. Este gráfico muestra la cantidad de proyectos según su etapa o estado dentro del ciclo de desarrollo, como por ejemplo idea, diseño, ejecución o ejecución finalizada. De esta forma es posible observar en qué fases se concentra el mayor número de iniciativas.

A continuación, se presenta el gráfico “Iniciativas por proceso”, que muestra de forma horizontal la distribución de proyectos según el proceso administrativo o técnico en el que se encuentran. Entre estos procesos pueden encontrarse estudios previos, preparación del proyecto, obtención de aprobación técnica, ejecución, licitación u otros estados intermedios. Esta información permite comprender con mayor detalle el avance administrativo de las iniciativas.

En la parte inferior del panel se incluyen dos paneles comparativos. El primero muestra el avance general de actividades por sector, permitiendo visualizar el porcentaje de avance físico de las iniciativas agrupadas por área temática. El segundo panel presenta el avance financiero general por sector, que indica el nivel de ejecución presupuestaria de los proyectos dentro de cada sector.

Finalmente, el panel incorpora una tabla denominada “Top 5 iniciativas con mayor avance”, en la cual se listan los proyectos que presentan los mayores niveles de progreso dentro del sistema. Para cada iniciativa se muestra el monto invertido, el avance de sus actividades y el avance financiero asociado.

En conjunto, este cuadro de mando permite a los usuarios obtener una visión consolidada del estado de las iniciativas del plan, facilitando el seguimiento general, la identificación de tendencias y el apoyo a la toma de decisiones dentro de la gestión municipal.

Gestión de iniciativas

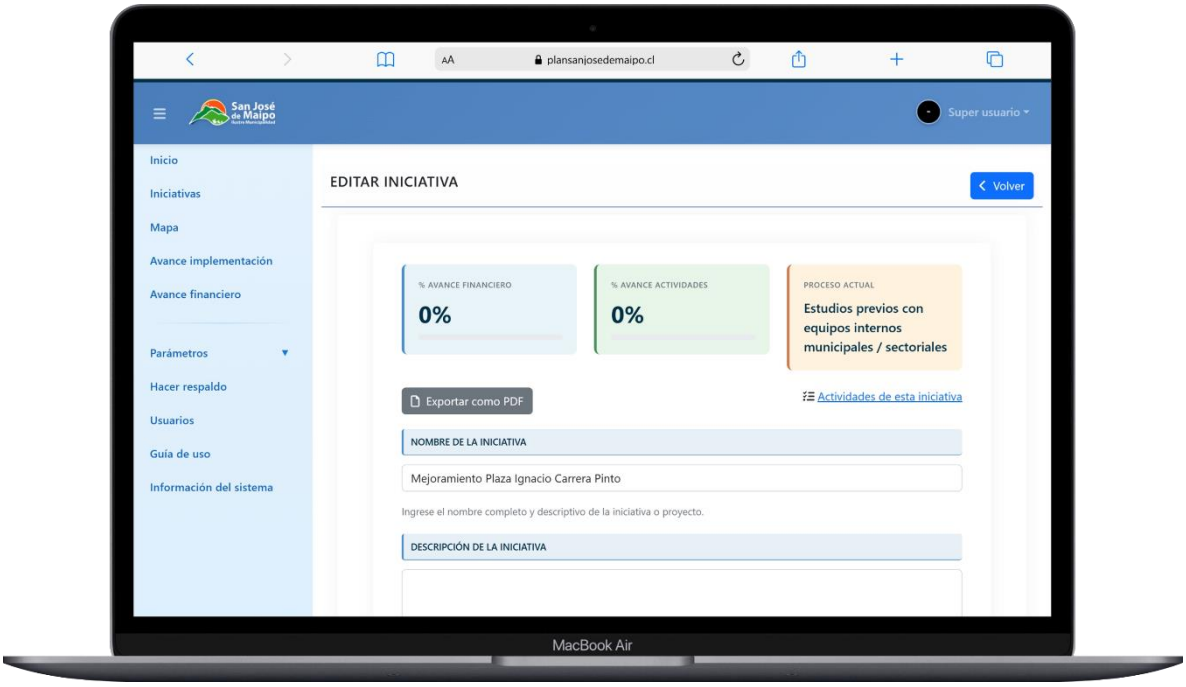

La gestión de iniciativas es la funcionalidad central del sistema, ya que permite registrar, consultar y actualizar la información asociada a los proyectos que forman parte del plan de inversión del municipio. A través de esta sección, los usuarios autorizados pueden administrar el ciclo completo de cada iniciativa, desde su registro inicial hasta el seguimiento de su ejecución.

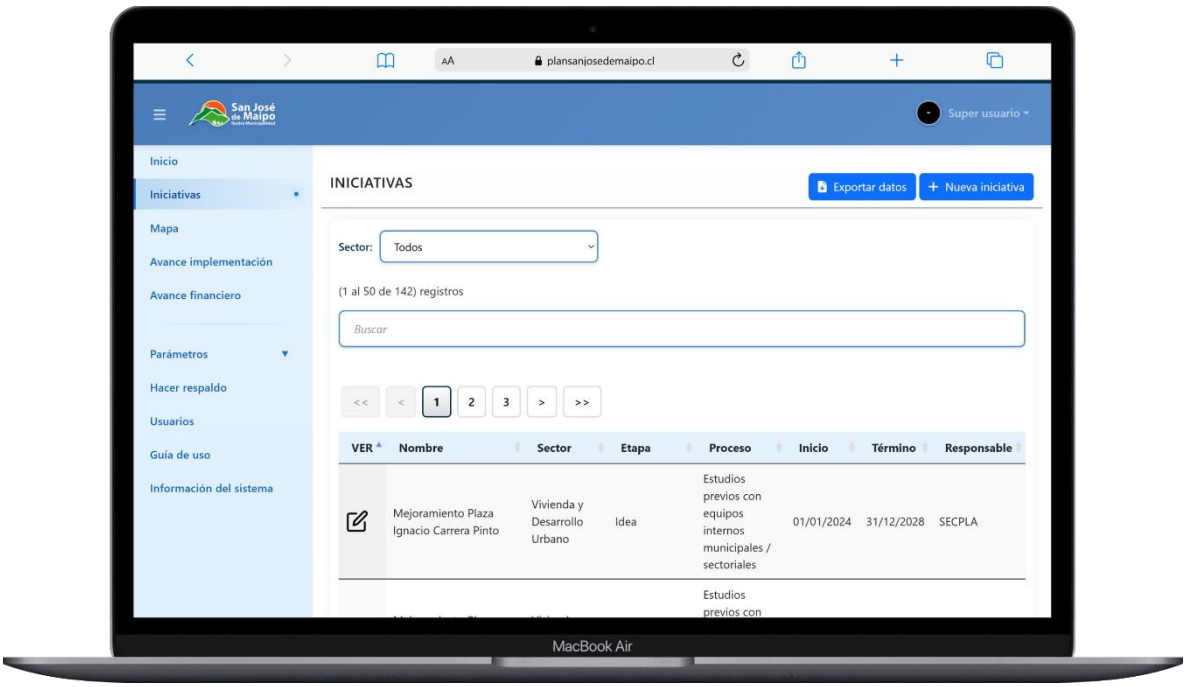

El acceso a esta funcionalidad se realiza desde la opción “Iniciativas” del menú principal. Al ingresar, el sistema presenta una lista de todas las iniciativas registradas en la plataforma. Esta lista permite visualizar información general de cada proyecto, como su nombre, sector al que pertenece, etapa de desarrollo, proceso en el que se encuentra, fechas de inicio y término, y la unidad responsable. La tabla incluye herramientas de búsqueda, filtrado por sector y paginación, lo que facilita localizar rápidamente una iniciativa específica dentro del conjunto de proyectos registrados.

Desde esta misma vista es posible crear nuevas iniciativas mediante la opción correspondiente ubicada en la parte superior de la pantalla. Asimismo, cada registro de la lista cuenta con un acceso directo que permite abrir la ficha de edición del proyecto para consultar o modificar su información.

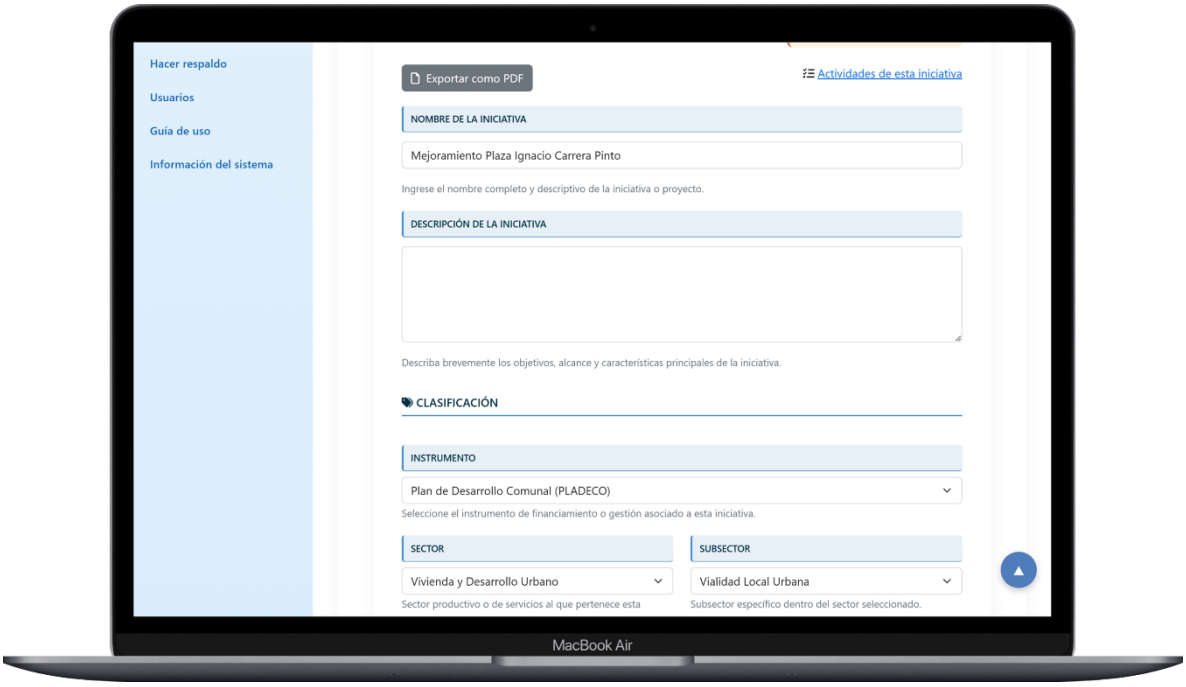

La ficha de la iniciativa constituye el espacio donde se almacena y administra toda la información del proyecto. En ella se organizan distintos bloques de información que permiten registrar los principales antecedentes de la iniciativa. Entre estos se incluyen el nombre del proyecto, una descripción general, la clasificación del proyecto según instrumento, sector, subsector y tipo, así como información financiera relacionada con el presupuesto de diseño y ejecución.

La ficha también incorpora un apartado de cronograma y estado, donde se registra la etapa de desarrollo de la iniciativa, el proceso administrativo o técnico en el que se encuentra y las fechas estimadas de inicio y término. Esta información permite situar el proyecto dentro de su ciclo de desarrollo y facilitar su seguimiento.

Otro componente relevante corresponde a la sección de responsabilidad y vinculación, donde se registra la fuente de financiamiento del proyecto, la unidad municipal responsable de su

ejecución y otras instituciones relacionadas con la iniciativa. Estos datos permiten identificar claramente a las entidades involucradas en el desarrollo del proyecto.

El sistema también incluye información relativa al avance del proyecto, donde se muestran indicadores de avance financiero y de avance de actividades. Estos valores se calculan automáticamente en función de la información registrada en las actividades asociadas a la iniciativa.

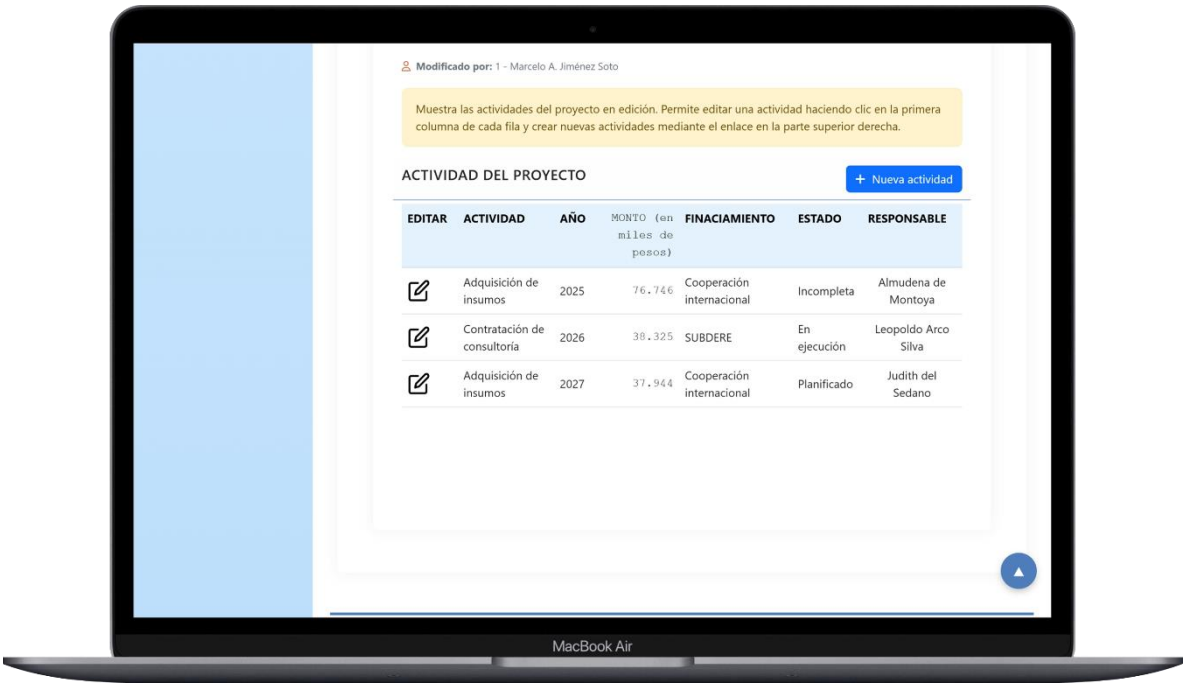

En la parte inferior de la ficha se encuentra la sección “Actividades del proyecto”, donde es posible gestionar las distintas tareas que componen la iniciativa. Cada actividad puede incluir información como el año de ejecución, el monto asociado, la fuente de financiamiento, su estado de avance y el responsable de su ejecución. Desde esta sección los usuarios pueden crear nuevas actividades o editar las existentes, lo que permite llevar un seguimiento detallado del progreso del proyecto.

Finalmente, la ficha incorpora un apartado de geolocalización, donde se registran las coordenadas geográficas del proyecto. Esta información permite que la iniciativa sea representada en el mapa interactivo del sistema, facilitando su visualización territorial.

En conjunto, la gestión de iniciativas permite mantener organizada y actualizada la información de los proyectos municipales, proporcionando una herramienta estructurada para su seguimiento y administración dentro del sistema.

Edición de actividades de las iniciativas

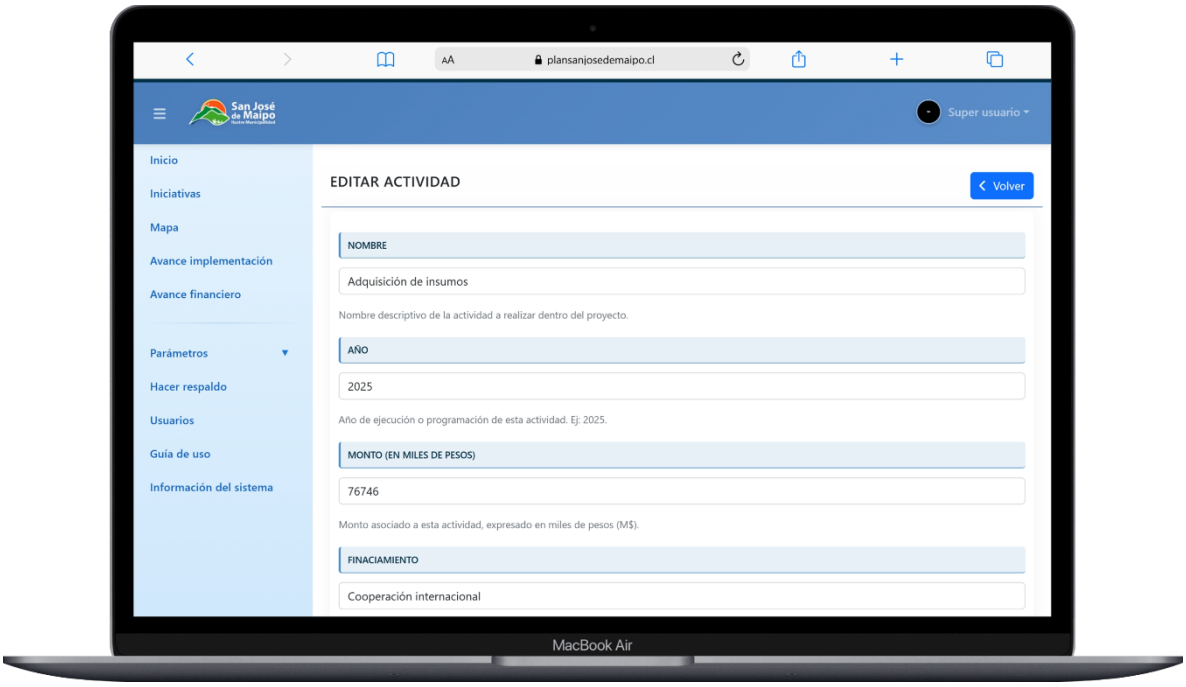

La edición de actividades permite registrar y actualizar la información de las tareas específicas que forman parte de una iniciativa o proyecto dentro del sistema. Cada actividad representa una acción concreta que contribuye al desarrollo o ejecución del proyecto, por lo que su correcta actualización es fundamental para reflejar el avance real de la iniciativa.

Para acceder a la edición de una actividad, el usuario debe ingresar a la ficha de la iniciativa correspondiente y dirigirse a la sección “Actividades del proyecto”. Desde allí es posible seleccionar una actividad existente para modificar su información o registrar una nueva.

La pantalla de edición de actividad presenta un formulario compuesto por diversos campos que permiten registrar los principales antecedentes asociados a la actividad.

El primer campo corresponde al Nombre, donde se debe ingresar una descripción breve de la actividad a realizar dentro del proyecto, por ejemplo “Adquisición de insumos” u otra acción específica relacionada con la ejecución de la iniciativa.

A continuación se encuentra el campo Año, que indica el año en que se ejecuta o se programa la actividad. Este dato permite ordenar temporalmente las acciones del proyecto y facilitar su planificación.

El campo Monto (en miles de pesos) permite registrar el presupuesto asociado a la actividad. El valor ingresado se expresa en miles de pesos (M$), lo que facilita el manejo de montos dentro del sistema y su posterior análisis financiero.

Posteriormente se incluye el campo Financiamiento, donde se especifica la fuente de financiamiento que respalda la actividad. Entre los ejemplos posibles se encuentran financiamiento municipal, sectorial, FNDR u otras fuentes externas.

El campo Responsable permite registrar el nombre de la persona o unidad encargada de ejecutar o supervisar la actividad dentro del proyecto. Esta información ayuda a identificar claramente quién tiene a cargo el desarrollo de la tarea.

El formulario también incluye el campo Estado, que permite indicar si la actividad se encuentra completa o incompleta. Este dato es relevante, ya que el estado de cada actividad influye directamente en el cálculo del avance general del proyecto dentro del sistema.

Adicionalmente, existe la opción de adjuntar un documento en formato PDF, el cual puede utilizarse como respaldo de la actividad, por ejemplo para incorporar informes, contratos, actas u otros documentos relacionados con su ejecución.

El sistema también muestra el campo Última actualización, donde se registra automáticamente la fecha y hora de la última modificación realizada en la actividad.

Una vez realizados los cambios necesarios, el usuario puede seleccionar la opción “Guardar cambios” para actualizar la información registrada. En caso de que la actividad deba eliminarse, el sistema dispone del botón “Eliminar actividad”, el cual permite removerla del proyecto.

Mediante esta funcionalidad, el sistema facilita el seguimiento detallado de las tareas que componen cada iniciativa, permitiendo mantener actualizada la información sobre su ejecución y contribuyendo a una gestión más ordenada y transparente de los proyectos del plan de inversión.

Informe de estado de avance de implementación

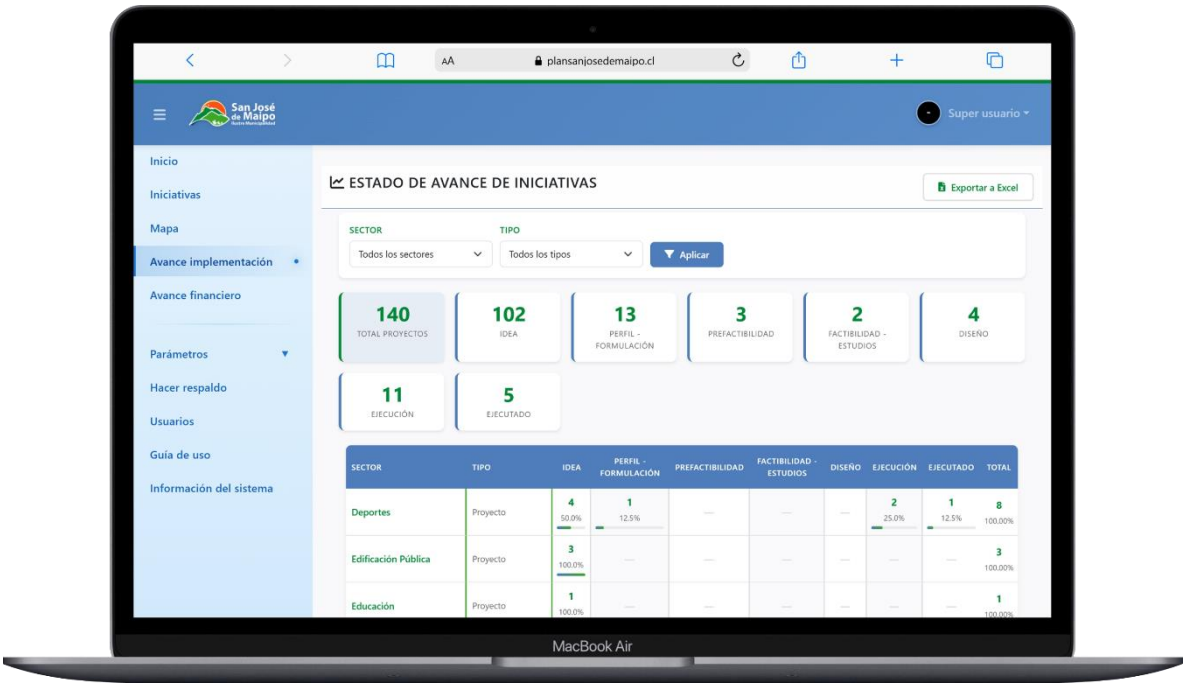

El informe de estado de avance de implementación permite visualizar el progreso de las iniciativas registradas en el sistema según la etapa en la que se encuentran dentro de su ciclo de desarrollo. Esta sección ofrece una vista consolidada que facilita el seguimiento general de los proyectos y permite identificar rápidamente en qué fase se concentran las iniciativas del plan de inversión.

En la parte superior de la pantalla se encuentran herramientas de filtrado, que permiten acotar la información presentada según distintos criterios. Los usuarios pueden seleccionar un sector específico y un tipo de iniciativa, aplicando posteriormente el filtro mediante el botón correspondiente. Esto permite analizar el avance de los proyectos de forma más focalizada, por ejemplo revisando únicamente los proyectos de un sector determinado.

Debajo de los filtros se presenta un conjunto de indicadores resumidos, los cuales muestran la cantidad total de iniciativas registradas y su distribución según las distintas etapas de desarrollo. Entre estas etapas se encuentran, por ejemplo, idea, perfil o formulación, prefactibilidad, factibilidad o estudios, diseño, ejecución y ejecutado. Estos indicadores permiten obtener rápidamente una visión general del estado en que se encuentran los proyectos dentro del sistema.

La sección principal del informe corresponde a una tabla de distribución por sector, donde se presenta el detalle de iniciativas agrupadas según el sector al que pertenecen. Para cada sector se muestra el tipo de iniciativa y la cantidad de proyectos que se encuentran en cada una de las etapas del ciclo de desarrollo.

Cada celda de la tabla incluye tanto el número de iniciativas como un indicador porcentual, representado mediante una barra visual que facilita interpretar la proporción de proyectos en cada etapa dentro del sector correspondiente. Esto permite identificar con claridad qué áreas presentan un mayor número de iniciativas en fases tempranas de planificación o en etapas más avanzadas de ejecución.

En la parte inferior de la tabla se incluye una fila de totales, que resume la distribución global de todas las iniciativas registradas en el sistema, mostrando la cantidad y el porcentaje total de proyectos en cada etapa.

Adicionalmente, el sistema incorpora la opción de exportar la información a Excel mediante el botón “Exportar a Excel”, ubicado en la parte superior del informe. Esta funcionalidad permite descargar los datos del reporte en formato de hoja de cálculo, facilitando su análisis, procesamiento o incorporación en informes externos.

En conjunto, este informe constituye una herramienta útil para el monitoreo del avance de implementación del plan, permitiendo a los usuarios evaluar el estado de las iniciativas y apoyar la toma de decisiones en la gestión de la inversión municipal.

Informe de avance financiero

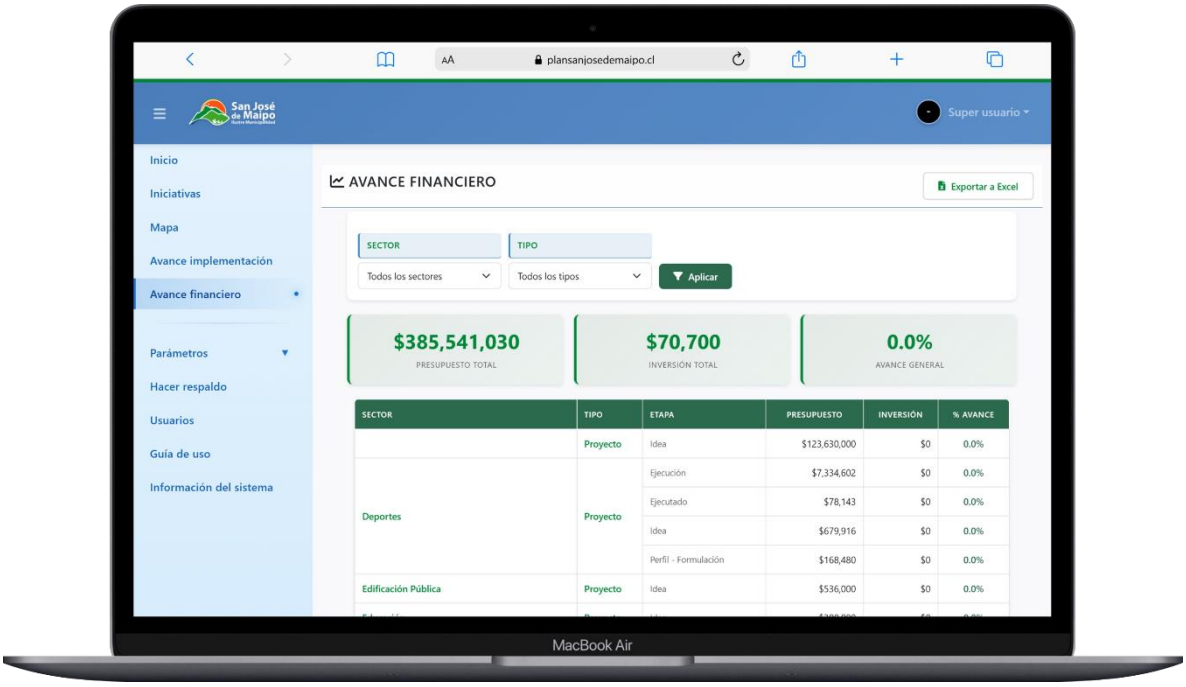

El informe de avance financiero permite visualizar el estado de ejecución presupuestaria de las iniciativas registradas en el sistema. Esta sección entrega una visión general del nivel de inversión asociado a los proyectos del plan, permitiendo analizar cuánto presupuesto se ha comprometido y ejecutado en relación con los montos totales planificados.

En la parte superior del informe se encuentran herramientas de filtrado, que permiten acotar la información presentada según distintos criterios. Los usuarios pueden seleccionar un sector específico y un tipo de iniciativa, lo que facilita revisar la ejecución financiera de un grupo particular de proyectos. Una vez seleccionados los filtros, la información se actualiza al presionar el botón “Aplicar”.

Debajo de los filtros se presentan indicadores resumidos que muestran los principales valores financieros del conjunto de iniciativas. Estos indicadores permiten visualizar de forma rápida el monto total asociado a los proyectos, el monto efectivamente invertido y el porcentaje general de avance financiero del plan de inversión.

La sección principal del informe corresponde a una tabla de distribución financiera por sector, donde se muestran las iniciativas agrupadas según el sector al que pertenecen. Para cada sector se presenta información relacionada con los montos comprometidos y ejecutados, así como el nivel de avance financiero alcanzado.

Cada fila de la tabla permite observar el comportamiento financiero de los proyectos dentro de un sector determinado, incluyendo indicadores visuales que ayudan a interpretar de manera rápida el porcentaje de ejecución presupuestaria. Estos indicadores facilitan identificar sectores con mayor nivel de inversión ejecutada y aquellos que aún se encuentran en etapas iniciales de gasto.

En la parte inferior de la tabla se presenta una fila de totales, que resume los valores globales del conjunto de iniciativas incluidas en el informe, permitiendo obtener una visión consolidada del estado financiero del plan de inversión.

Al igual que otros reportes del sistema, el informe de avance financiero incorpora la opción de exportar los datos a Excel mediante el botón “Exportar a Excel”, ubicado en la parte superior de la pantalla. Esta funcionalidad permite descargar la información en formato de hoja de cálculo para su análisis externo, elaboración de reportes o integración en documentos de gestión.

En conjunto, este informe constituye una herramienta clave para el seguimiento de la ejecución presupuestaria de las iniciativas, permitiendo a los usuarios monitorear el uso de los recursos y apoyar la toma de decisiones en la gestión financiera del plan de inversión municipal.

Parámetros del sistema

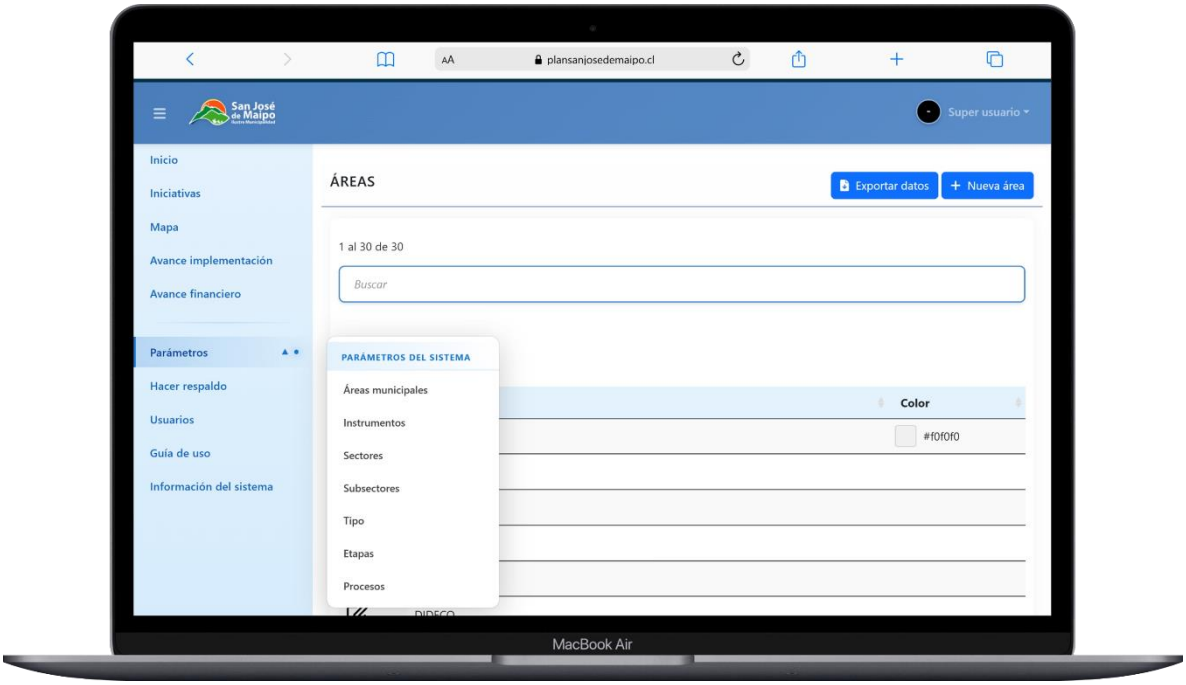

El sistema incluye una sección denominada Parámetros, destinada a la administración de los distintos valores de clasificación utilizados para organizar la información de las iniciativas. Estos parámetros permiten estructurar los proyectos dentro de categorías comunes, lo que facilita su registro, análisis y visualización dentro de la plataforma.

Dentro de esta sección se encuentran los siguientes tipos de parámetros:

- Áreas municipales: corresponden a las unidades o direcciones del municipio responsables de la gestión o ejecución de las iniciativas. Estos valores permiten

asociar cada proyecto a una unidad municipal específica y también se utilizan para gestionar permisos de edición de los usuarios.

- Instrumentos: permiten clasificar las iniciativas según el instrumento de planificación o programa al cual pertenecen, facilitando su identificación dentro del marco de planificación municipal.
- Sectores: representan las áreas temáticas a las que pertenecen los proyectos, como por ejemplo educación, salud, transporte, turismo, entre otros. Esta clasificación permite agrupar las iniciativas según su ámbito de intervención.
- Subsectores: corresponden a subdivisiones dentro de cada sector, permitiendo una clasificación más específica de las iniciativas.
- Tipo: define la naturaleza o categoría del proyecto, diferenciando por ejemplo distintos tipos de iniciativas según su carácter o modalidad de intervención.
- Etapas: representan las fases del ciclo de desarrollo de los proyectos, tales como idea, formulación, prefactibilidad, diseño, ejecución, entre otras. Estas etapas permiten identificar el nivel de desarrollo de cada iniciativa.
- Procesos: describen los distintos estados administrativos o técnicos por los que puede pasar un proyecto durante su desarrollo, por ejemplo preparación, revisión, aprobación o licitación.

Cada uno de estos parámetros puede ser visualizado, creado o editado desde su respectiva sección dentro del menú de parámetros. La información se gestiona mediante listados simples que permiten agregar nuevos registros, modificar los existentes o eliminarlos en caso de ser necesario.

Sin embargo, estos parámetros se encuentran precargados en el sistema, ya que forman parte de la estructura base utilizada para clasificar las iniciativas del plan de inversión. Debido a que corresponden a categorías relativamente estables y con pocos registros, la interacción con esta información suele ser mínima y normalmente solo se requiere realizar modificaciones en casos excepcionales, como la incorporación de una nueva categoría o un ajuste en la estructura de clasificación.

En este sentido, la sección de parámetros funciona principalmente como un módulo de configuración del sistema, permitiendo mantener ordenada la estructura de clasificación de las iniciativas sin requerir una administración frecuente por parte de los usuarios.

Mapa interactivo

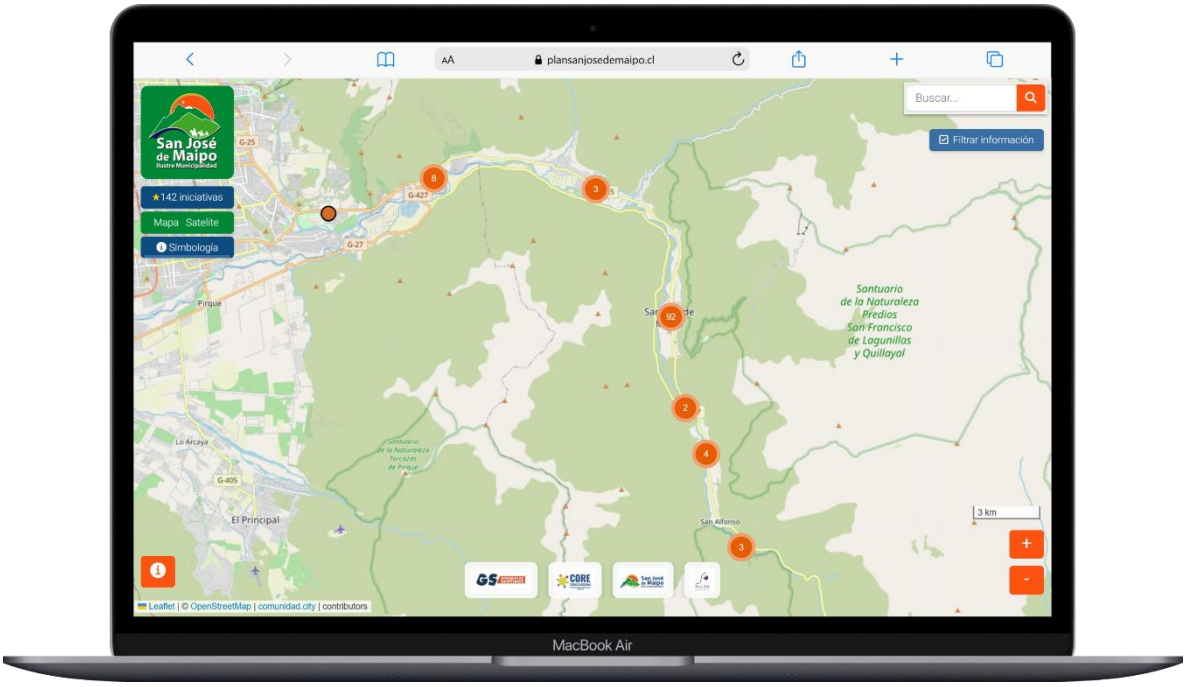

El mapa interactivo es la cara pública del sistema y permite a la ciudadanía visualizar de forma georreferenciada la ubicación de las iniciativas del Plan Maestro de Inversión de la comuna. Su acceso es libre y no requiere credenciales, pudiendo consultarse desde cualquier dispositivo con conexión a internet, ya sea un computador, una tableta o un teléfono móvil.

La información que muestra el mapa se nutre directamente de los datos registrados en el sistema de gestión por el personal municipal, por lo que se mantiene actualizada a medida que los proyectos avanzan en su ejecución.

Cada iniciativa se representa en el mapa mediante un círculo de color, donde el color identifica el área de clasificación a la que pertenece el proyecto. Cuando en una misma ubicación se concentran varias iniciativas, el círculo muestra un número que indica la cantidad de proyectos asociados a ese punto. Al hacer clic sobre un círculo, el mapa despliega una ficha con la información detallada de la iniciativa, incluyendo su sector, subsector, etapa de desarrollo, proceso actual, porcentaje de avance financiero y porcentaje de avance de actividades. Desde esta ficha es posible continuar navegando hacia el detalle completo del proyecto mediante el botón "Continuar".

En la parte superior derecha del mapa se encuentra el botón "Filtrar información", que permite acotar los proyectos visualizados según distintos criterios, facilitando la búsqueda de iniciativas de interés. Adicionalmente, existe un buscador en la esquina superior derecha para localizar proyectos o lugares específicos dentro del territorio.

El panel lateral izquierdo muestra el total de iniciativas registradas e incluye opciones para alternar entre la vista de mapa base y la vista satelital. También incorpora el botón "Simbología", que explica el significado de los colores utilizados en la representación de los

proyectos. Los controles de zoom ubicados en la esquina inferior derecha permiten acercar o alejar la vista del mapa para explorar el territorio con mayor o menor detalle.

Desde una perspectiva de gestión pública, la georreferenciación de los proyectos agrega una dimensión que los informes tradicionales no ofrecen: permite ver el territorio. Es posible identificar visualmente si la inversión se concentra en determinadas zonas de la comuna, si ciertos sectores rurales o periféricos cuentan con menor cantidad de iniciativas, o si existe una distribución equilibrada entre distintos tipos de proyectos. Esta lectura territorial puede ser un insumo valioso para la planificación futura y para fundamentar decisiones de priorización de inversión.

Finalmente, la existencia de un sistema de este tipo envía una señal institucional importante: que el municipio asume un compromiso con la rendición de cuentas y con mantener informada a su comunidad. La posibilidad de que cualquier vecino pueda verificar en tiempo real el avance de los proyectos que afectan su entorno cotidiano fortalece la confianza entre la institución y la ciudadanía, y sienta las bases para una participación más informada y constructiva en los asuntos públicos de la comuna.

Respaldo de base de datos

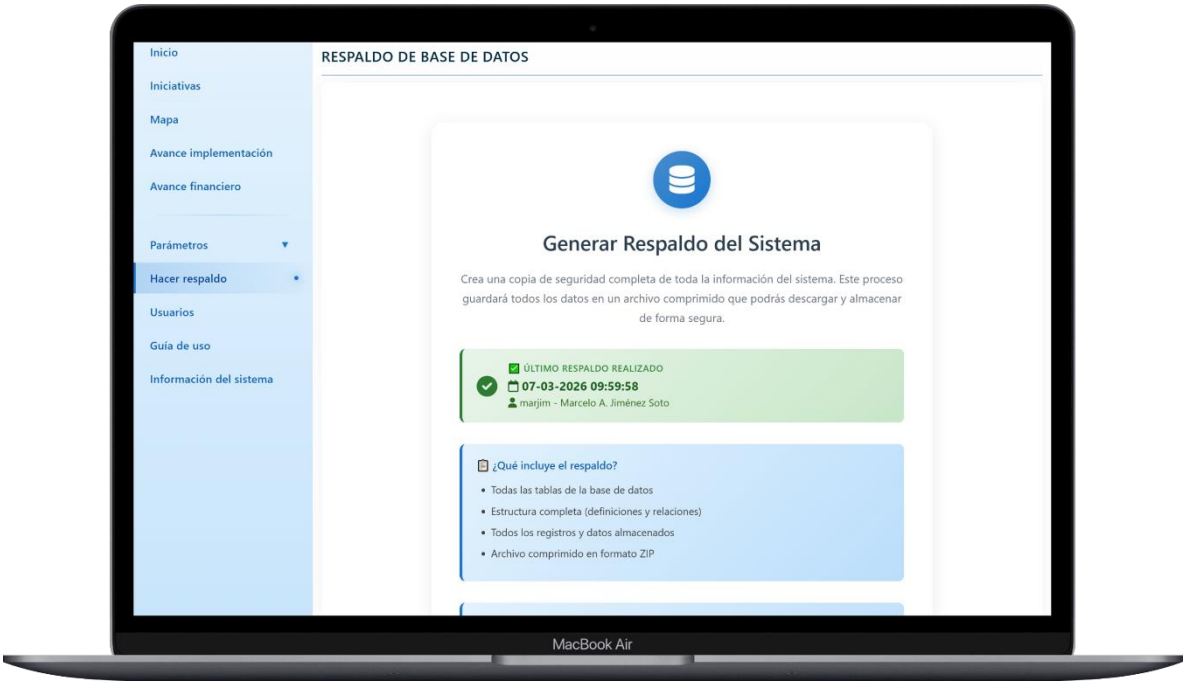

El sistema incorpora una funcionalidad que permite generar respaldos de la base de datos, con el objetivo de resguardar toda la información almacenada en la plataforma. Esta herramienta permite crear una copia de seguridad completa del sistema, lo que resulta fundamental para proteger los datos ante posibles fallas técnicas, errores humanos o necesidades de restauración futura.

El acceso a esta función se realiza desde la opción “Hacer respaldo” del menú de administración. Esta herramienta está disponible únicamente para usuarios con perfil de administrador, ya que implica la gestión directa de la información completa del sistema.

Al generar un respaldo, el sistema crea automáticamente un archivo que contiene todas las tablas de la base de datos, incluyendo su estructura (definiciones y relaciones) y todos los registros almacenados. Esta copia se genera en un archivo comprimido en formato ZIP, el cual puede ser descargado y almacenado de forma segura por el administrador.

La pantalla también muestra información sobre el último respaldo realizado, indicando la fecha, la hora y el usuario que ejecutó la operación. Esto permite llevar un control básico de las copias de seguridad generadas dentro del sistema.

Para generar un nuevo respaldo, el administrador solo debe seleccionar el botón “Generar y Descargar Respaldo”. Una vez ejecutada esta acción, el sistema procesa la información y genera el archivo de respaldo, el cual se descarga automáticamente al dispositivo del usuario.

Se recomienda realizar respaldos de forma periódica, por ejemplo semanal o mensualmente, y guardar los archivos generados en un lugar seguro. Asimismo, es aconsejable verificar que la descarga del archivo se haya completado correctamente para asegurar que la copia de seguridad se encuentre disponible en caso de ser necesaria.

Esta funcionalidad contribuye a mantener la seguridad y continuidad de la información, permitiendo recuperar los datos del sistema en caso de incidentes o requerimientos de restauración.

Gestión de usuarios

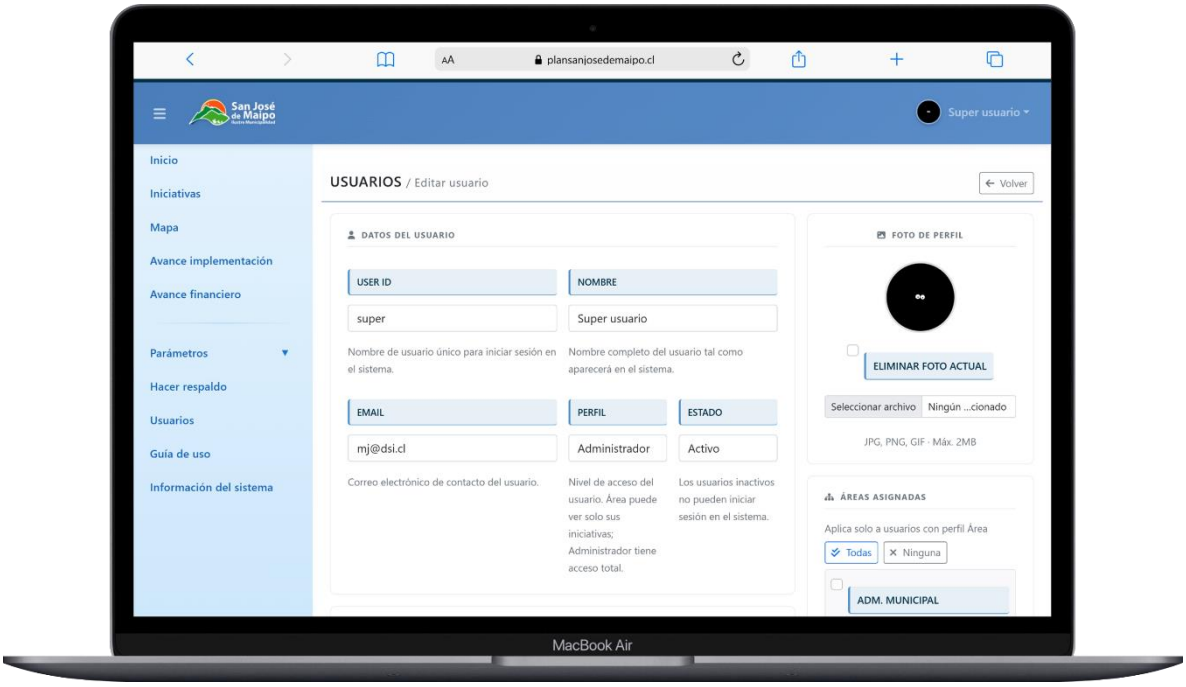

La gestión de usuarios permite administrar las cuentas de acceso al sistema. A través de esta sección, el usuario con perfil de administrador puede crear nuevas cuentas, modificar los datos de usuarios existentes, asignar perfiles de acceso y controlar el estado de cada cuenta dentro de la plataforma.

El acceso a esta funcionalidad se realiza desde la opción "Usuarios" del menú de administración. Al ingresar, el sistema presenta una lista con todos los usuarios registrados, donde es posible visualizar su identificador, nombre completo, correo electrónico, perfil asignado y la fecha y hora del último acceso al sistema. La tabla incluye un buscador que permite filtrar los resultados según el texto ingresado, así como controles de paginación para navegar entre los registros cuando el número de usuarios es elevado.

Desde esta misma vista es posible crear un nuevo usuario mediante el botón "+ Nuevo usuario", ubicado en la parte superior de la pantalla. Asimismo, cada registro de la lista cuenta con un acceso directo que permite abrir el formulario de edición del usuario correspondiente.

El formulario de edición se organiza en distintas secciones. La sección "Datos del usuario" contiene los campos principales: el identificador de usuario (User ID), que es el nombre único utilizado para iniciar sesión; el nombre completo del usuario; su correo electrónico de contacto; el perfil de acceso asignado; y el estado de la cuenta, que puede ser activo o inactivo. Los usuarios con estado inactivo no pueden iniciar sesión en el sistema.

La sección "Seguridad" permite gestionar la contraseña del usuario. Al activar la opción correspondiente, se habilitan los campos para ingresar una nueva contraseña. Adicionalmente, existe la opción de obligar al usuario a cambiar su contraseña en el próximo acceso, lo que resulta útil al crear cuentas nuevas o al restablecer credenciales.

En el panel lateral del formulario se encuentra la sección de foto de perfil, donde es posible cargar una imagen asociada al usuario en formato JPG, PNG o GIF, con un tamaño máximo de 2 MB. También es posible eliminar la foto existente marcando la opción correspondiente antes de guardar los cambios.

Áreas asignadas

La sección "Áreas asignadas" aplica exclusivamente a usuarios con perfil Área y permite definir a qué áreas municipales tendrá acceso el usuario para editar iniciativas. Es posible asignar todas las áreas, ninguna, o realizar una selección específica según las responsabilidades del usuario dentro del municipio.

Finalmente, la sección "Registro" muestra información de auditoría no editable: la fecha y hora de la última modificación del perfil y la fecha y hora del último acceso registrado al sistema.

Una vez realizados los cambios necesarios, el administrador puede guardar la información mediante el botón "Guardar cambios". En caso de que sea necesario eliminar la cuenta, el sistema dispone del botón "Eliminar usuario", el cual remueve definitivamente el registro de la plataforma.

Perfiles de usuario

El sistema contempla tres perfiles de acceso que determinan las funcionalidades disponibles para cada usuario.

El perfil Administrador dispone de acceso completo al sistema. Puede crear y gestionar usuarios, administrar los parámetros del sistema, generar respaldos de la base de datos y consultar o editar la información de todas las iniciativas registradas, independientemente del área a la que pertenezcan.

El perfil Área tiene acceso restringido a las iniciativas correspondientes a las áreas municipales que le han sido asignadas. Puede consultar y editar únicamente los proyectos vinculados a su área de responsabilidad, mientras que las iniciativas de otras áreas permanecen disponibles solo para consulta.

El perfil Invitado permite el acceso de solo lectura al sistema. Los usuarios con este perfil pueden navegar y consultar la información disponible en la plataforma, pero no pueden realizar modificaciones sobre los datos registrados.

Información del sistema

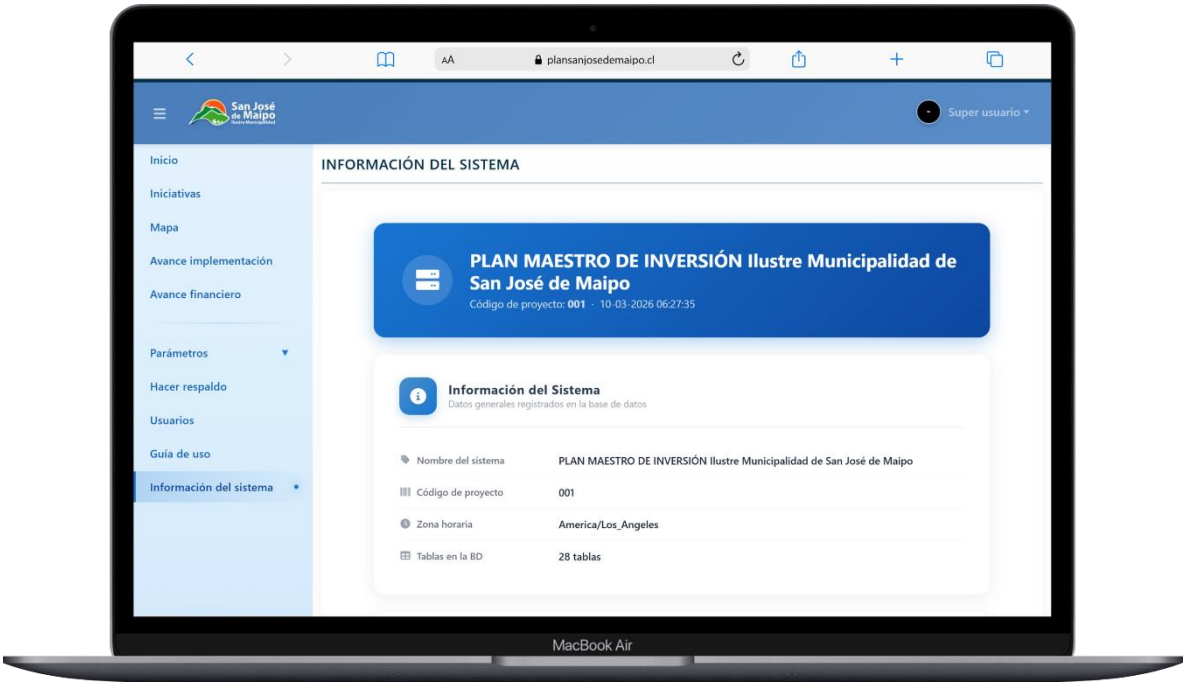

La sección Información del sistema entrega una vista consolidada de los datos técnicos y de configuración de la plataforma. Esta pantalla está disponible únicamente para usuarios con perfil de administrador y tiene como propósito proporcionar una referencia rápida sobre el estado general del sistema y su entorno de operación.

La pantalla se organiza en cuatro bloques de información. El primero corresponde a los datos generales del sistema, donde se indica el nombre del proyecto, el código de proyecto asignado, la zona horaria configurada y la cantidad de tablas registradas en la base de datos.

El segundo bloque muestra información sobre el último respaldo realizado, indicando la fecha y hora en que fue generado y el usuario que ejecutó la operación. Esta información permite verificar rápidamente si las copias de seguridad se están realizando con la periodicidad adecuada.

El tercer bloque presenta los datos del entorno PHP del servidor, incluyendo la versión del intérprete instalada, el límite de memoria asignado y los tamaños máximos permitidos para la subida de archivos y el envío de datos mediante formularios.

El cuarto bloque describe el servidor y la base de datos, indicando el servidor web utilizado, el sistema operativo del servidor, el nombre del host y la versión del motor de base de datos MySQL instalado.

Esta sección no permite realizar modificaciones y cumple exclusivamente una función informativa, orientada al monitoreo técnico de la plataforma por parte del administrador del sistema.

Consideraciones finales

El sistema de gestión, seguimiento y georreferenciación de iniciativas del Plan Maestro de Inversión constituye una herramienta de trabajo diseñada para apoyar la labor cotidiana del municipio en la administración de sus proyectos. Su valor, sin embargo, depende directamente de la calidad y oportunidad con que se actualice la información que contiene. Un sistema bien mantenido refleja fielmente la realidad de la inversión comunal; uno desactualizado pierde progresivamente su utilidad tanto para la gestión interna como para la ciudadanía.

Por ello, es fundamental que los usuarios responsables de cada área mantengan al día la información de las iniciativas a su cargo, especialmente en lo que respecta al avance de actividades, el estado de los procesos y los datos financieros. La periodicidad con que se actualice esta información determinará en gran medida la confiabilidad de los reportes, la precisión del mapa público y la utilidad del panel de control como herramienta de toma de decisiones.

Se recomienda también realizar respaldos de la base de datos de forma regular, verificar periódicamente que los usuarios registrados correspondan al personal activo del municipio, y mantener actualizados los parámetros del sistema cuando se incorporen nuevas categorías o cambien las estructuras de clasificación existentes.

Ante cualquier dificultad técnica, consulta sobre el funcionamiento del sistema o necesidad de soporte, los usuarios pueden contactar al administrador del sistema o al equipo responsable de su mantención.